#1 Wylew / zalanie terenu + erozja [2025-06-05]

Priorytet: KRYTYCZNY | MNDWI +33% | NDWI +14% | NDTI +3% | NDVI -7%

Mapa + MNDWI z-score

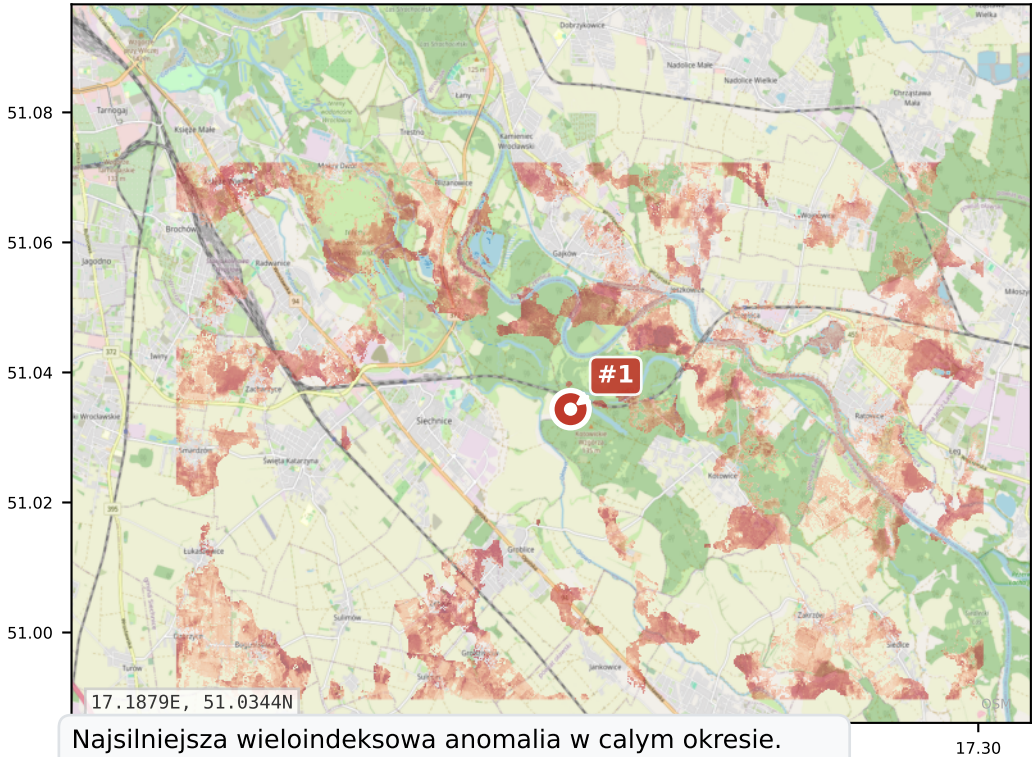

MNDWI z-score — 2025-06-05

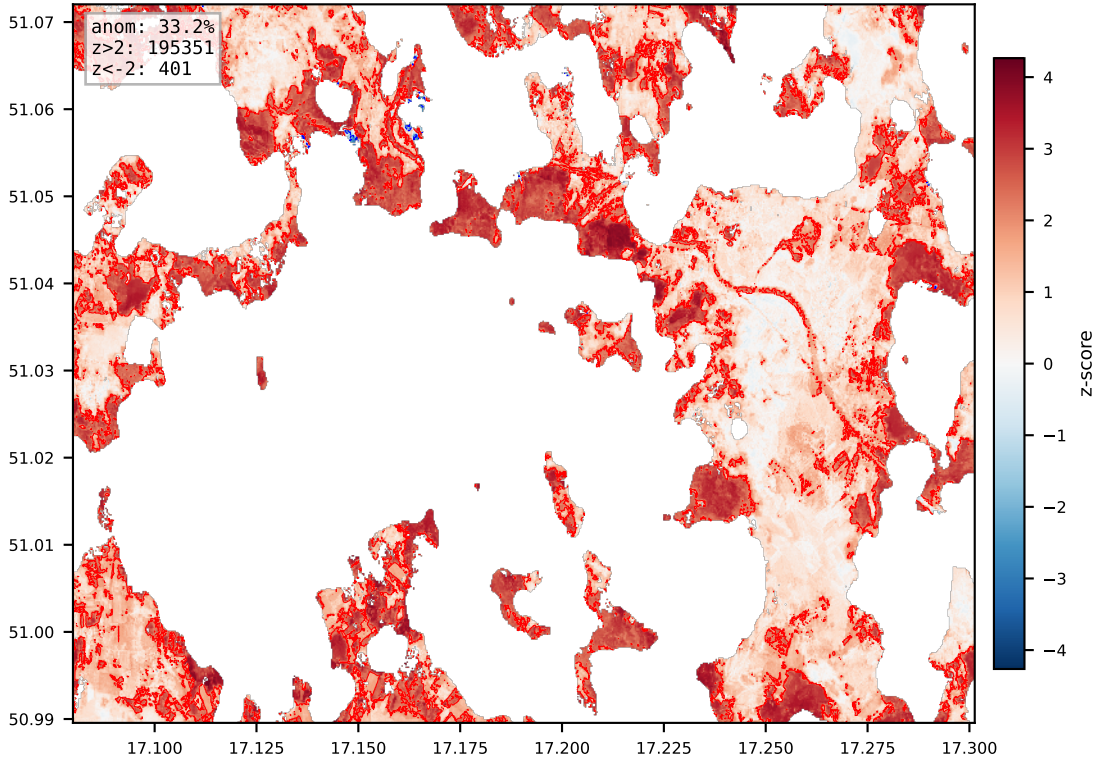

Najsilniejsza wieloindeksowa anomalia w calym okresie. 6 z 6 indeksow wykazuje odchylenia. MNDWI wzrasta o 33% pikseli ponad 2-sigma, co wskazuje na masowy wzrost zasiegu wody na terenie. Jednoczesnie NDVI spada (-7%), co potwierdza podtopienie roslinnosci.

NDTI rowniez wzrasta (+3%) — woda niesie zawiesine, typowe dla splywow erozyjnych po intensywnych opadach. SAR potwierdza: VV_wzrost 5.3% pikseli.

INTERPRETACJA: Prawdopodobnie gwaltowne opady deszczu spowodowaly wylew lokalnych ciekow wodnych w rejonie Siechnic. Woda zalala pola i laki, niosac ze soba zmyte osady glebowe (stad wzrost zmetnienia NDTI).

#2 Zrzut sciekow do cieku wodnego [2025-06-23]

Priorytet: WYSOKI | NDTI +4% | NDCI +1% | MNDWI +14% | NDVI -3%

Mapa + NDTI z-score

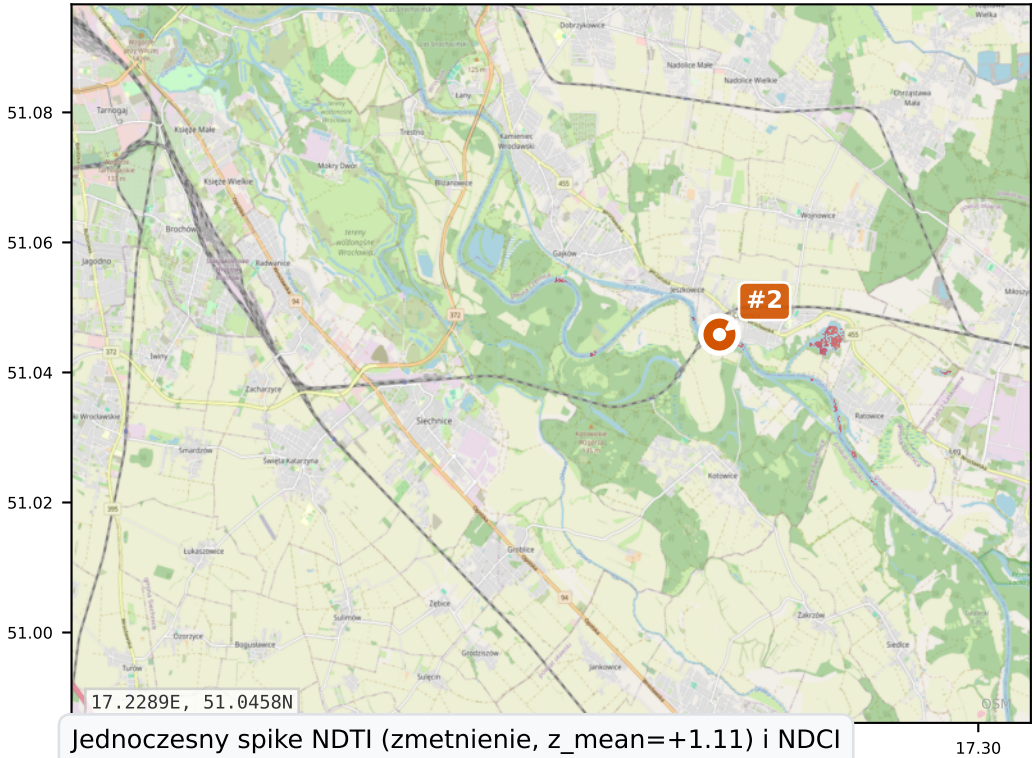

NDTI z-score — 2025-06-23

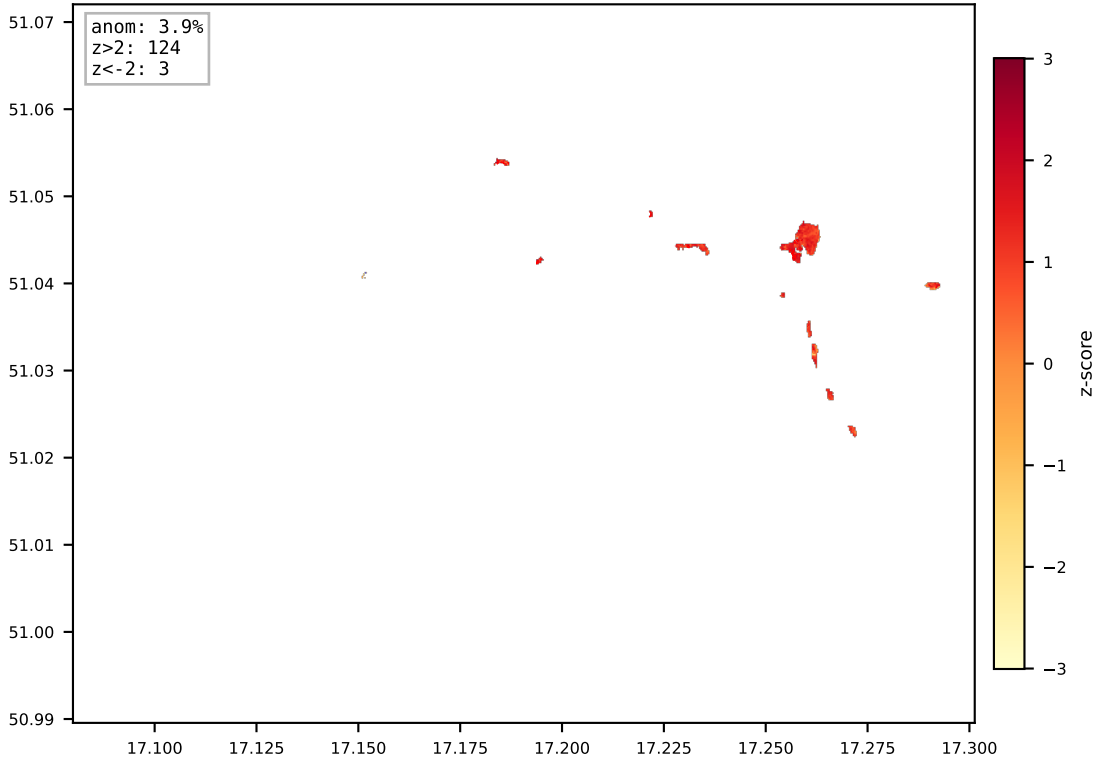

Jednoczesny spike NDTI (zmetnienie, z_mean=+1.11) i NDCI (chlorofil, z_mean=+0.73) — to klasyczna sygnatura chemiczna zrzutu sciekow bogatych w skladniki odzywcze.

NDTI+ oznacza gwaltowny wzrost mutnosci wody, a NDCI+ wskazuje na poczatek eutrofizacji — mikroorganizmy zaczynaja wykorzystywac azot i fosfor ze sciekow.

SAR VV_wzrost = 7.6% pikseli, co moze odzwierciedlac zmiane chropowatosci powierzchni wody.

INTERPRETACJA: Mozliwy zrzut sciekow komunalnych lub przemyslowych do lokalnego cieku. Lokalizacja centroidu anomalii (17.19E, 51.03N) wskazuje na rejon polnocny dorzecza Odry w Siechnicach.

#3 Zrzut sciekow — powtorne zdarzenie [2025-06-30]

Priorytet: WYSOKI | NDTI +9% | NDCI +2% | NDMI +10% | NDVI +13%

Mapa + NDTI z-score

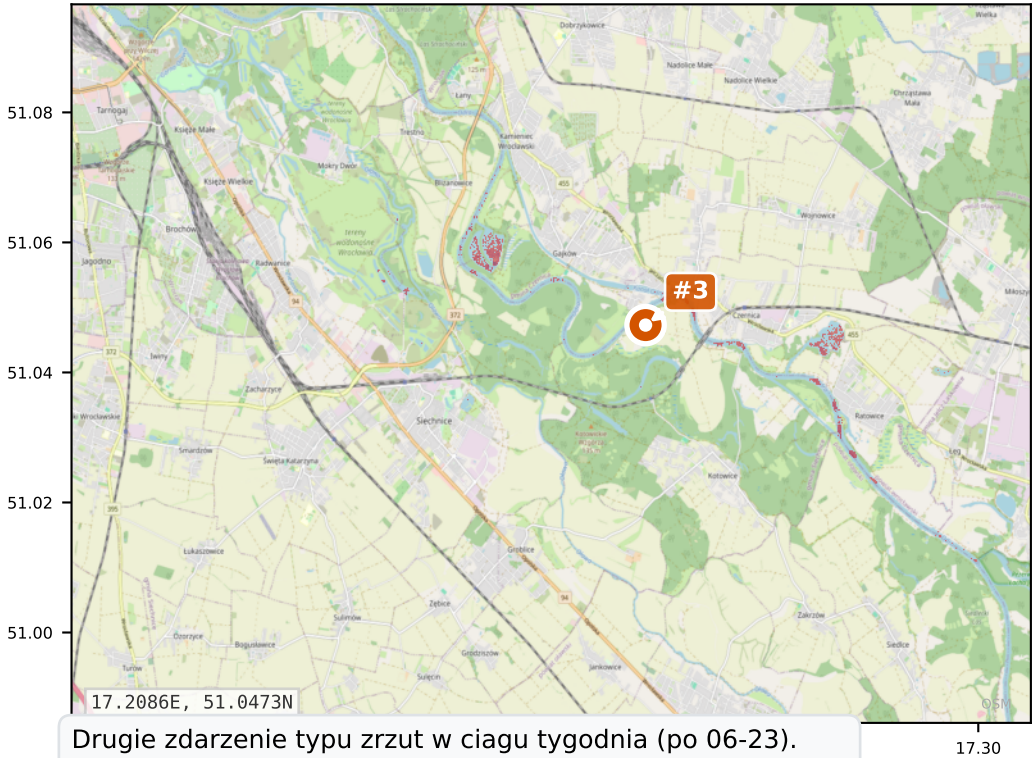

NDTI z-score — 2025-06-30

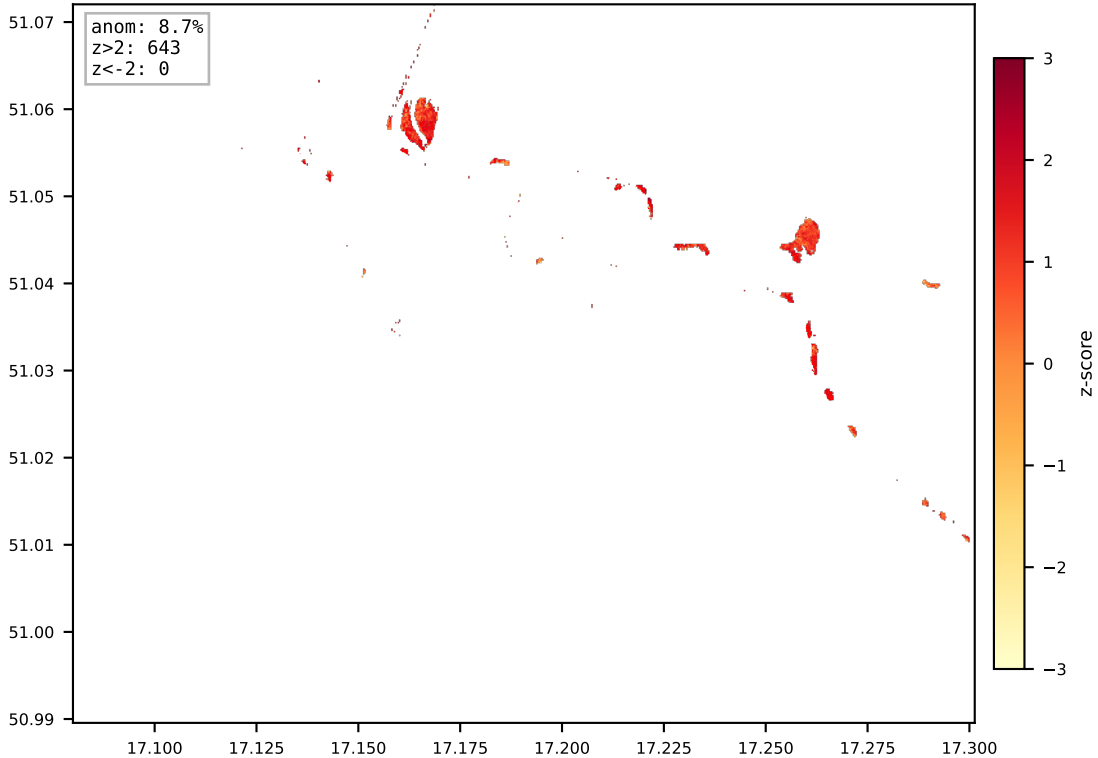

Drugie zdarzenie typu zrzut w ciagu tygodnia (po 06-23). NDTI spike +9% pikseli wody z z_mean=+1.12 — silny wzrost zmetnienia. NDCI +2% z z_mean=+0.39 potwierdza doprecyzowanie zrodla jako sciekow (nie czysta erozja).

Charakterystyczne: MNDWI lekko spada (z_mean=-0.71) ale NDMI rosnie (+10%) — mokra gleba wokol cieku. NDVI wzrasta (+13%) co moze wskazywac na bujny wzrost roslinnosci zasilanej skladnikami odzywczymi.

SAR: VV_wzrost 6.3%.

INTERPRETACJA: Powtarzajacy sie wzorzec zrzutu w tym samym rejonie (17.17E, 51.02N). Cyklicznosc sugeruje regularne odprowadzanie sciekow, nie incydent jednorazowy.

#4 Rozlegly wylew — tereny zalewowe [2025-05-06]

Priorytet: WYSOKI | MNDWI +43% | NDWI +20% | NDVI -13% | NDMI +5%

Mapa + MNDWI z-score

MNDWI z-score — 2025-05-06

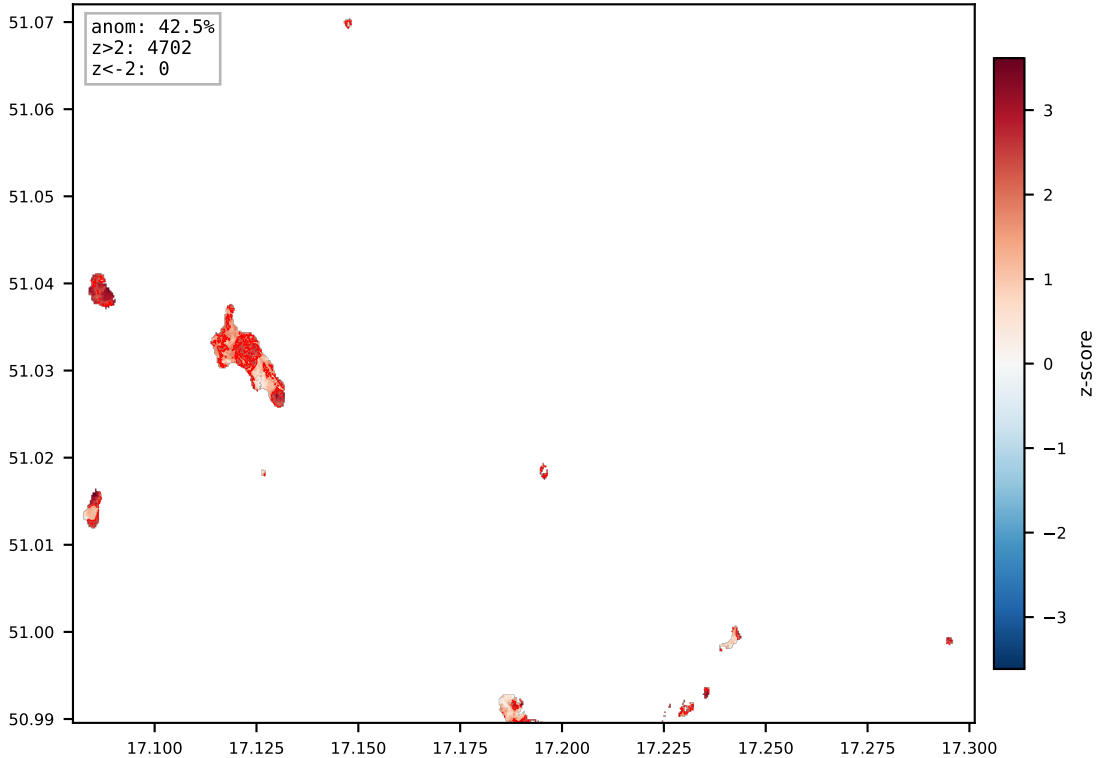

43% pikseli z anomalnym wzrostem MNDWI (z_mean=+1.82) i 20% pikseli NDWI — rozlegly wzrost zasiegu wody. Jednoczesnie NDVI spada w 13% pikseli — roslinnosc jest pod woda.

Centroid anomalii (17.13E, 51.03N) wskazuje na zachodnia czesc AOI — tereny zalewowe Odry/Olawki.

NDMI wzrasta +5% — zwiekszona wilgotnosc gleby na terenach sasiednich, nie bezposrednio zalanych.

INTERPRETACJA: Wiosenne wezbranie (maj). Podniesiony stan wod w dorzeczu Odry powoduje zalanie terenow zalewowych. Skala anomalii (43% MNDWI) wskazuje na rozlegle zjawisko hydrologiczne, nie punktowy wyciek.

#5 Spadek wody + bujny wzrost roslinnosci [2025-04-21]

Priorytet: SREDNI | NDVI +37% | NDWI -46% | MNDWI -17% | NDMI +2%

Mapa + NDVI z-score

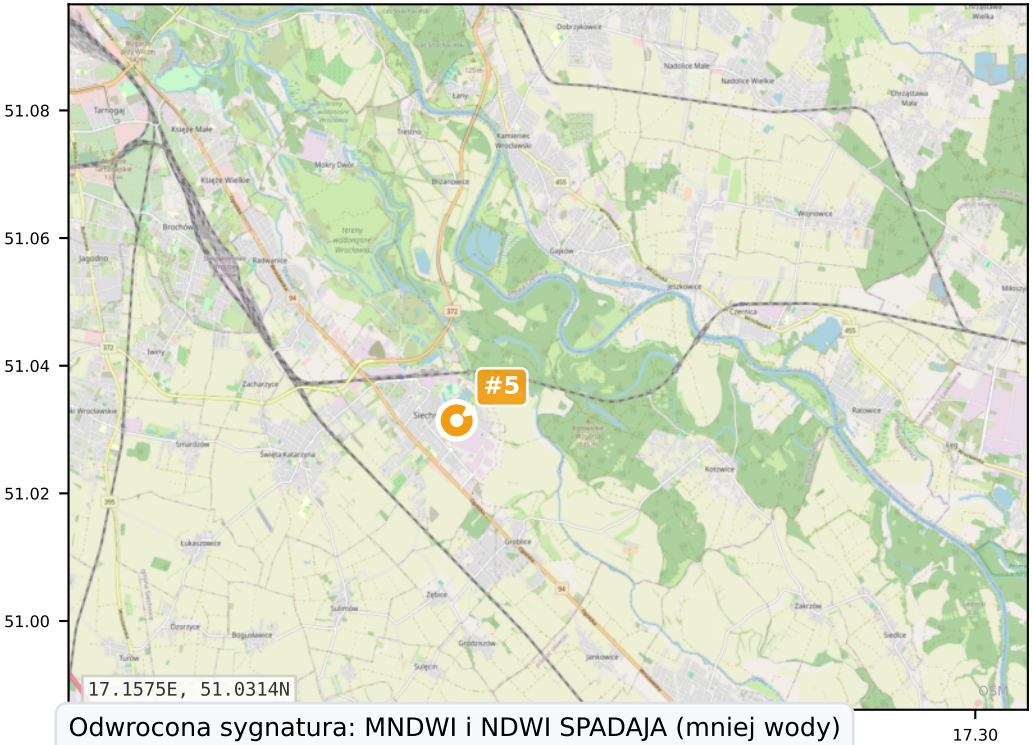

NDVI z-score — 2025-04-21

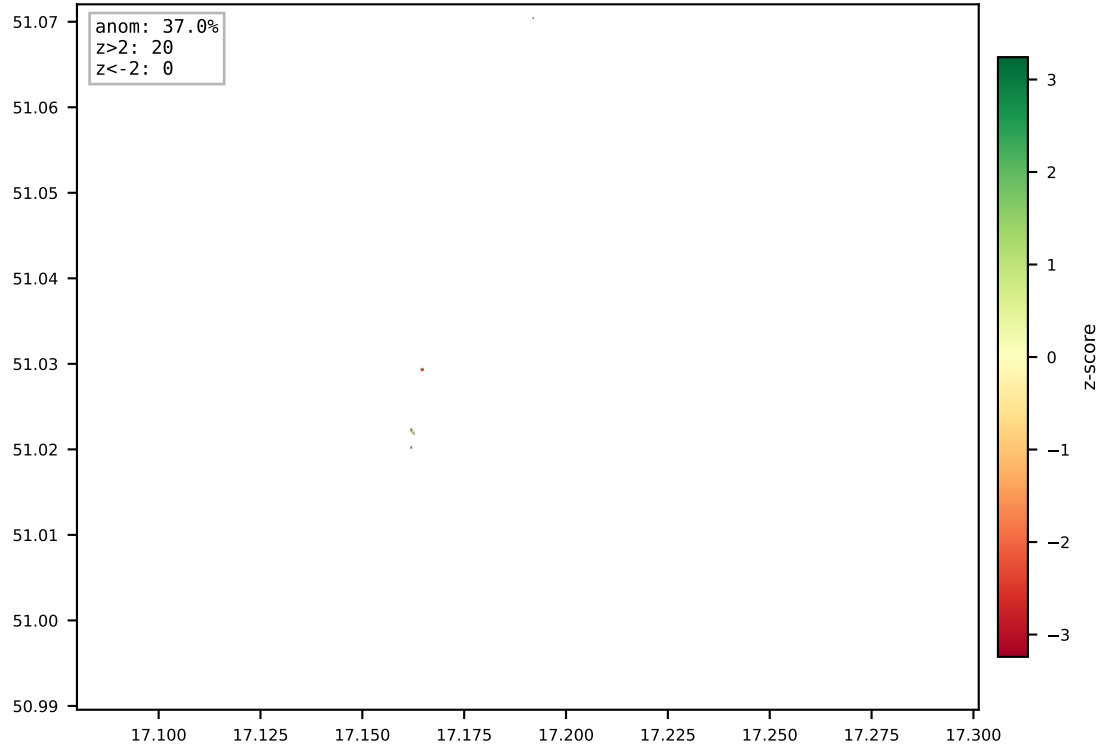

Odwrocona sygnatura: MNDWI i NDWI SPADAJA (mniej wody) a NDVI gwaltownie ROSNIE (+37% pikseli, z_mean=+1.77). To oznacza: zmniejszony zasieg wody przy jednoczesnym anomalnie bujnym wzroscie roslinnosci.

NDMI (wilgotnosc gleby) lekko podniesiony — gleba jest nawilzona mimo ze woda otwarta znika.

INTERPRETACJA:
Sygnatura NDVI++ / MNDWI-- / NDWI-- moze wskazywac na:
(a) Nawadnianie upraw z poboru wody — nielegalny lub nadmierny pobor z cieku/studni powoduje spadek poziomu wody, ale roslinnosc bujnie rosnie.
(b) Naturalne sezonowe wyschnięcie + wiosenny wzrost wegetacji (mniej podejrzane).

Wymaga korelacji z danymi o legalnych pozwoleniach wodnoprawnych w rejonie (17.16E, 51.03N).